งาน WEB-GIS

งานที่ได้รับมอบหมาย รายวิชา 426-315 ระบบสารสนเทศภูมิศาสตร์บนอินเทอร์เน็ต มีรายละเอียดดังนี้

1. ไฟล์ index.html สำหรับแสดงหน้าโฮมเพจเพื่อเชื่อมโยงและข้อมูลกับของต่าง ๆ
2. ไฟล์ page1.html สำหรับแสดงหน้าเพจ Administration List แสดงไฟล์ดังนี้
    - 2.1 Administration_list.php
    - 2.2 province2amp.php
    - 2.3 amp2tanbol.php
3. ไฟล์ page2.html สำหรับแสดงหน้าเพจ Tourism Information System แสดงไฟล์ดังนี้
    - 3.1 Create.php
    - 3.2 Read.php
    - 3.3 Update.php
    - 3.4 Delete.php
    - 3.5 conpolitic.php
    - 3.6 success_popup.php
    - 3.7 โฟลเดอร์ images (สำหรับบันทึกข้อมูลรูปภาพ และไฟล์ที่ผู้ใช้บันทึก)
4. ไฟล์ page3.html สำหรับแสดงหน้าเพจ Maps by Map API แสดงไฟล์ดังนี้
    - 4.1 map_api.html
    - 4.2 province.zip (สำหรับดึงข้อมูลในการแสดงแผนที่)
5. ไฟล์ viewer.html สำหรับแสดง Source Code ของไฟล์ต่าง ๆ
6. ไฟล์ Web_Structure.png สำหรับแสดงโครงสร้างเว็บไซต์

เพิ่มเติมรายละเอียดของเว็บไซต์ครับ เนื่องจากเมื่ออัพโหลดขึ้น GitHub แล้วไฟล์ไม่แสดงครับ แต่ไฟล์อื่นสามารถแสดง Source Code ได้ตามปกติครับ

1. หน้าแสดงผลของ page1.html

แสดงการเรียกข้อมูลในระบบฐานข้อมูล โดยในที่นี้ได้เรียกข้อมูลของจังหวัด อำเภอ และตำบล ตามลำดับ โดยเมื่อเลือกข้อมูลครบแล้วและทำการบันทึกจะแสดงข้อความ “บันทึกข้อมูลเรียบร้อยแล้ว” แต่หากเลือกข้อมูลไม่ครบจะแสดงข้อความ “กรุณาเลือกจังหวัด อำเภอ และตำบลให้ครบ”

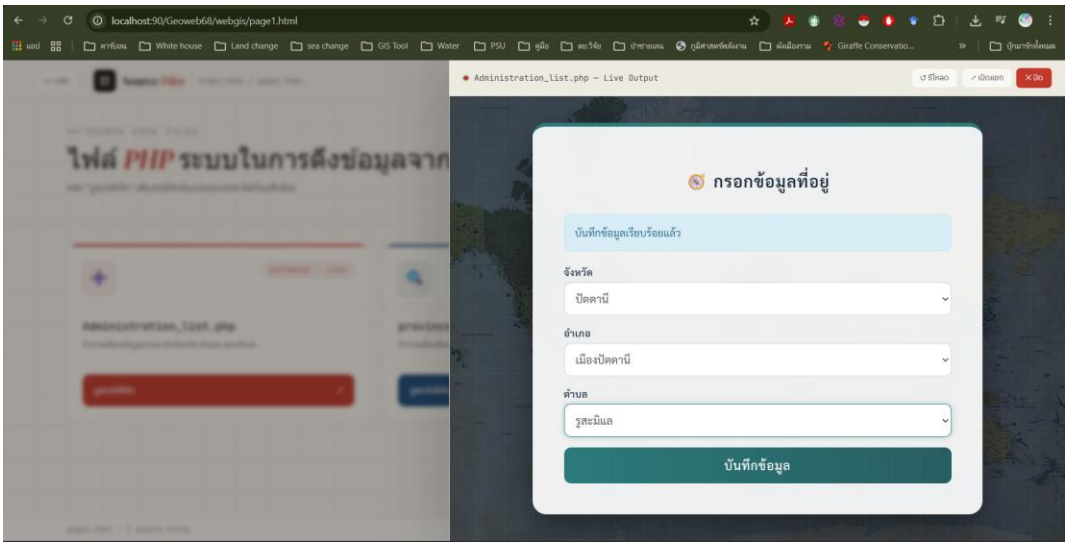

2. หน้าแสดงผลของ page2.html

แสดงการเรียกระบบบันทึกข้อมูลตามหลักของ CRUD เพื่อบันทึกข้อมูลของสถานที่ท่องเที่ยว เมื่อทำการบันทึกข้อมูลแล้วจะแสดงข้อความหน้าต่างข้อความแจ้งเตือนบันทึกข้อมูลสำเร็จ และจำนำไปสู่หน้าแสดงข้อมูลของสถานที่ และยังสามารถแก้ไขข้อมูลรวมทั้งสามารถลบข้อมูลที่ไม่ต้องการได้

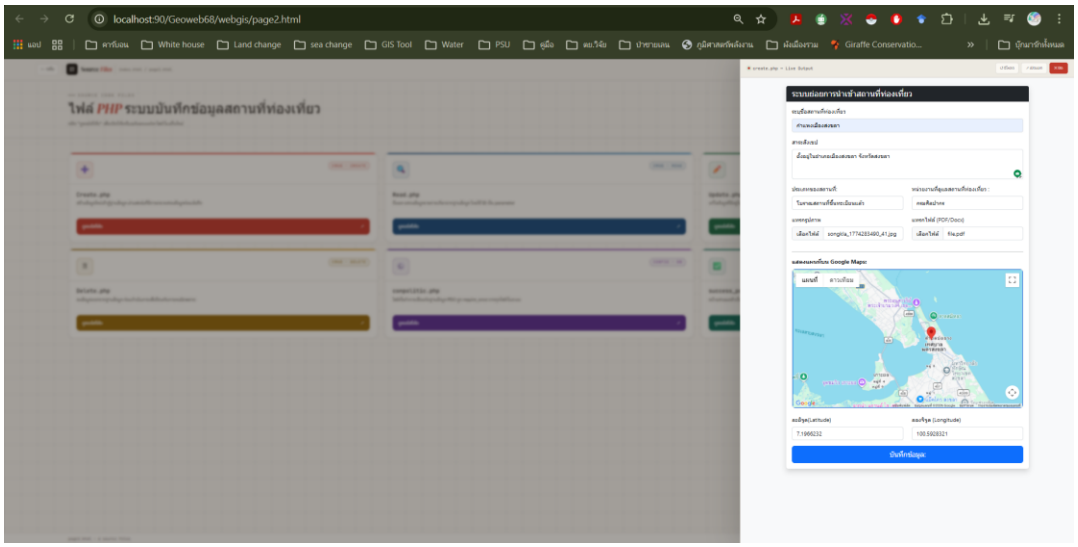

3. หน้าแสดงผลของ page3.html
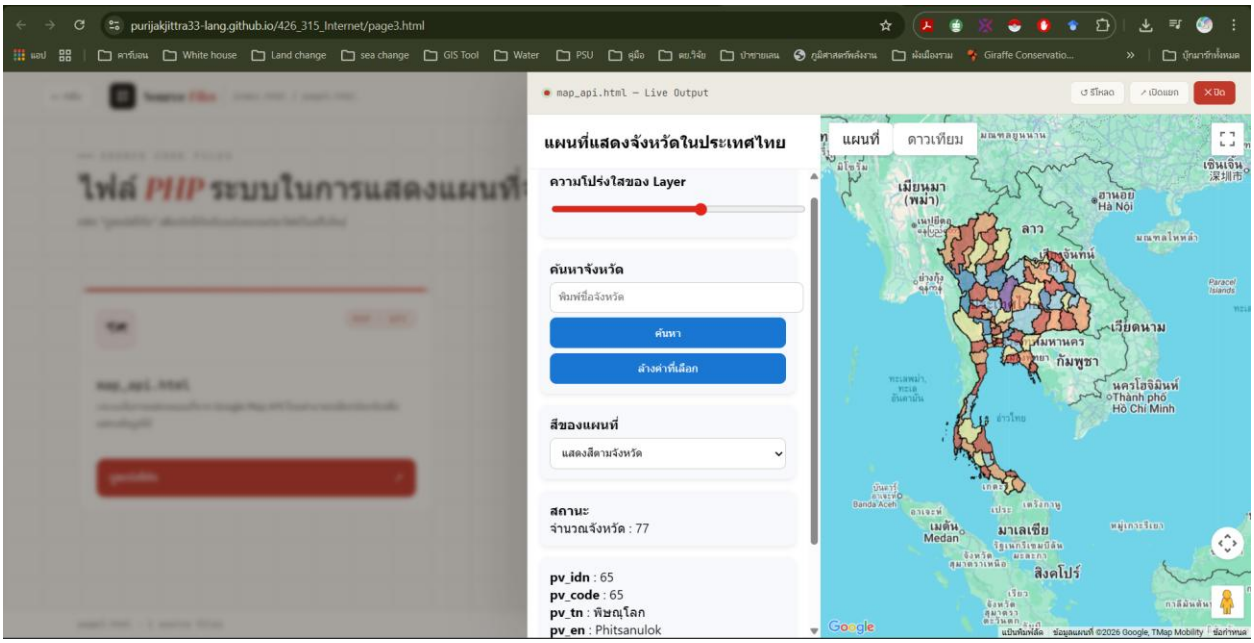
แสดงขอบเขตจังหวัดของประเทศไทยโดยใช้ Google Map API โดยสามารถเลือกจังหวัด รวมถึงค้นหาจังหวัดที่ต้องการเพื่อแสดงข้อมูลได้